Landesamt für Digitalisierung,
Breitband und Vermessung

ATK25
UK50
ATK 100
TK50
ÜK500

Amtliche
Topographische Karten
Umgebungskarten
Übersichtskarten



Kontakt

So erreichen Sie uns

Landesamt für Digitalisierung,
Breitband und Vermessung
Alexandrastraße 4
80538 München

U-Bahn	U4, U5 bis Lehel
Trambahn	Linie 16 bis Lehel
Bus	Linie 100 bis Nationalmuseum/Haus der Kunst
Internet	www.geodaten.bayern.de

Unser telefonischer Kundenservice

Mo – Do	8.00 –16.00 Uhr
Fr	8.00 –14.00 Uhr
Telefon	089 2129-1111
Fax	089 2129-1113
E-Mail	service@geodaten.bayern.de



Grundlage: Digitale Ortskarte (DOK)

Ausgabe 2021|2
Stand: Juli 2021

ATK25
Amtliche Topographische Karte im Maßstab 1 : 25 000

Freizeit im Detail



Foto: © Martin Antonov



Wer es genau wissen will, greift zur ATK25. Diese Kartenserie im Maßstab 1 : 25 000 bildet mit ihrer detaillierten Darstellung das komplette Verkehrsnetz mit allen Straßen und Wegen ab.
237 Einzelblätter stellen Bayern flächendeckend dar.
Ein Kartenblatt umfasst ca. 21 km x 22 km.

Was bietet die ATK25?

- individuelle Freizeitgestaltung mit allen ausgeschilderten Wander- und Radwanderwegen
- sichere Orientierung auch abseits der markierten Routen
- umfangreiches Spektrum an Freizeiteinrichtungen und Sehenswürdigkeiten
- anschauliche Wiedergabe der Geländeformen

Ausschnitt aus ATK25-Q12 Tegernsee

UK50
Umgebungskarte im Maßstab 1 : 50 000

Freizeit kompakt




Foto: © Martin Thum



Die Kartenserie UK50 im Maßstab 1 : 50 000 kombiniert den Vorteil einer großen Gebietsdarstellung mit der Wiedergabe eines vielfältigen Inhalts, der besonders auf die Bedürfnisse von Radfahrern und Wanderern abgestimmt ist.
52 Einzelblätter stellen Bayern flächendeckend dar.
Ein Kartenblatt umfasst ca. 50 km x 40 km.

Was bietet die UK50?

- genaue Rad- und Wandertourenplanung auf ausgeschilderten Wegen
- spezieller Blattschnitt für touristisch interessante Gebiete
- umfangreiches Spektrum an Freizeiteinrichtungen und Sehenswürdigkeiten
- anschauliche Wiedergabe der Geländeformen

Ausschnitt aus UK50-52 Tölzer Land – Starnberger See

ATK100
Amtliche Topographische Karte im Maßstab 1:100 000

Freizeit im Überblick



Foto: © Alina Bradford



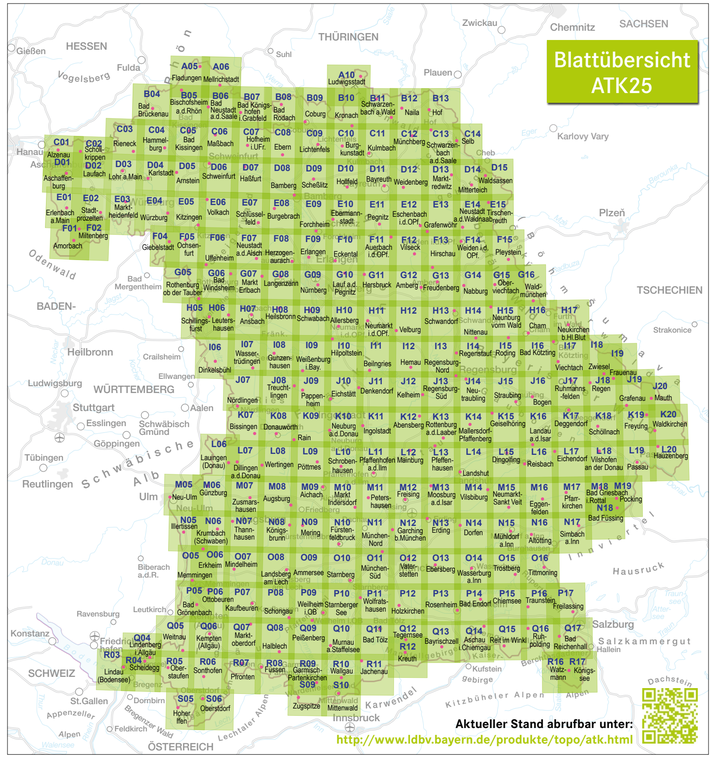
Für einen großräumigen Überblick bei weiten Touren liegt man mit der ATK100 genau richtig. Landschaftlich zusammenhängende Gebiete sind charakteristisch abgebildet, und der Karteninhalt ist auch im Maßstab 1 : 100 000 leicht verständlich.
19 Einzelblätter stellen Bayern flächendeckend dar.
Ein Kartenblatt umfasst ca. 85 km x 90 km.

Was bietet die ATK100?

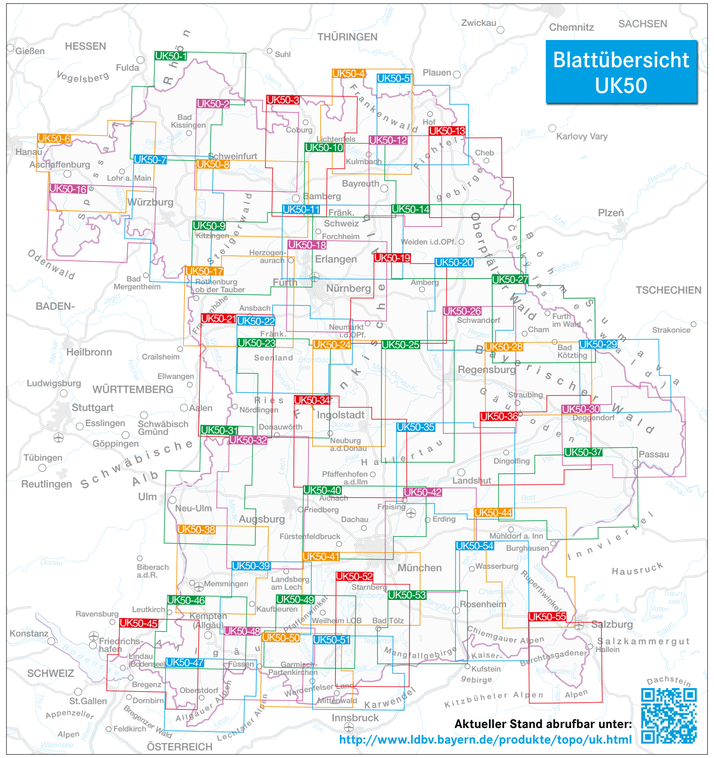
- weiträumige Tourenplanung auf den ausgeschilderten Fernrad- und Fernwanderwegen
- übersichtliche Darstellung großer Regionen
- umfangreiches Spektrum an Freizeiteinrichtungen und Sehenswürdigkeiten
- anschauliche Wiedergabe der Geländeformen

Ausschnitt aus ATK100-18 München Süd

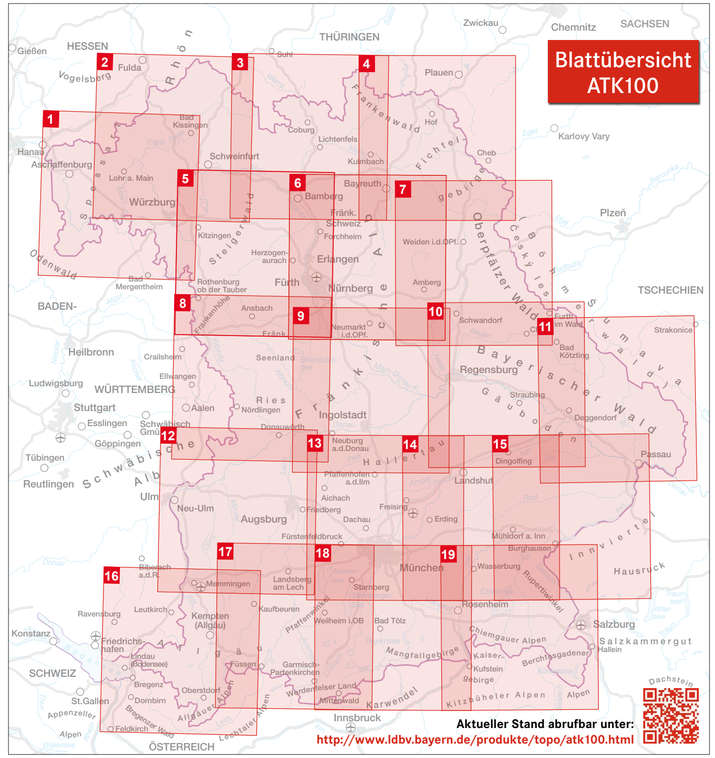
Blattübersicht ATK25



Blattübersicht UK50



Blattübersicht ATK100



Auflistung der ATK25-Kartenblätter

Blattnummer	Name	Erscheinungsjahr
ATK25-A05	Fladungen	2016
ATK25-A06	Mellrichstadt	2016
ATK25-A10	Ludwigsstadt	2021
ATK25-B04	Bad Brückenau	2021
ATK25-B05	Bischofsheim i.d.Rhön	2021
ATK25-B06	Bad Neustadt a.d.Saale	2021
ATK25-B07	Bad Königshofen i.Grabfeld	2021
ATK25-B08	Bad Rodach	2020
ATK25-B09	Coburg	2020
ATK25-B10	Kronach	2020
ATK25-B11	Schwarzenbach a.Wald	2021
ATK25-B12	Naila	2021
ATK25-B13	Hof	2021
ATK25-C01	Alzenau	2021
ATK25-C02	Schöllkrippen	2021
ATK25-C03	Rieneck	2021
ATK25-C04	Hammelburg	2021
ATK25-C05	Bad Kissingen	2021
ATK25-C06	Maßbach	2019
ATK25-C07	Hofheim i.UFr.	2017
ATK25-C08	Ebern	2017
ATK25-C09	Lichtenfels	2016
ATK25-C10	Burgkunstadt	2016
ATK25-C11	Kulmbach	2021
ATK25-C12	Münchberg	2018
ATK25-C13	Schwarzenbach a.d.Saale	2021
ATK25-C14	Selb	2021
ATK25-D01	Aschaffenburg	2021
ATK25-D02	Laufach	2020
ATK25-D03	Lohr a.Main	2020
ATK25-D04	Karlstadt	2021
ATK25-D05	Arnstein	2021
ATK25-D06	Schweinfurt	2019
ATK25-D07	Haßfurt	2018
ATK25-D08	Bamberg	2017
ATK25-D09	Scheßlitz	2016
ATK25-D10	Hollfeld	2016
ATK25-D11	Bayreuth	2018
ATK25-D12	Weidenberg	2018
ATK25-D13	Marktredwitz	2020
ATK25-D14	Mitterteich	2021
ATK25-D15	Waldsassen	2021
ATK25-E01	Erlenbach a.Main	2016
ATK25-E02	Stadtprozelten	2017
ATK25-E03	Marktheidenfeld	2017
ATK25-E04	Würzburg	2021
ATK25-E05	Kitzingen	2021
ATK25-E06	Volkach	2020
ATK25-E07	Schlüsselfeld	2020
ATK25-E08	Burgebrach	2019
ATK25-E09	Forchheim	2019
ATK25-E10	Ebermannstadt	2019
ATK25-E11	Pegnitz	2019
ATK25-E12	Eschenbach i.d.OPf.	2020
ATK25-E13	Grafenwöhr	2020
ATK25-E14	Neustadt a.d.Waldnaab	2020
ATK25-E15	Tirschenreuth	2020
ATK25-F01	Amorbach	2017
ATK25-F02	Miltenberg	2017
ATK25-F04	Giebelstadt	2016
ATK25-F05	Ochsenfurt	2016
ATK25-F06	Uffenheim	2020
ATK25-F07	Neustadt a.d.Aisch	2020
ATK25-F08	Herzogenaurach	2019
ATK25-F09	Erlangen	2019
ATK25-F10	Eckental	2019
ATK25-F11	Auerbach i.d.OPf.	2019
ATK25-F12	Vilseck	2019
ATK25-F13	Hirschau	2020
ATK25-F14	Weiden i.d.OPf.	2020
ATK25-F15	Pleystein	2020
ATK25-G05	Rothenburg ob der Tauber	2017
ATK25-G06	Bad Windsheim	2021
ATK25-G07	Markt Erlbach	2021
ATK25-G08	Langenzenn	2017
ATK25-G09	Nürnberg	2016
ATK25-G10	Lauf a.d.Pegnitz	2019
ATK25-G11	Hersbruck	2019
ATK25-G12	Amberg	2019
ATK25-G13	Freudenberg	2020
ATK25-G14	Nabburg	2020
ATK25-G15	Oberviechtach	2020
ATK25-G16	Waldmünchen	2020
ATK25-H05	Schillingsfürst	2018
ATK25-H06	Leutershausen	2016
ATK25-H07	Ansbach	2021
ATK25-H08	Heilsbronn	2018
ATK25-H09	Schwabach	2018
ATK25-H10	Allersberg	2019
ATK25-H11	Neumarkt i.d.OPf.	2019
ATK25-H12	Velburg	2019
ATK25-H13	Schwandorf	2019
ATK25-H14	Nittenau	2019
ATK25-H15	Neunburg vorm Wald	2020
ATK25-H16	Cham	2020
ATK25-H17	Neukirchen b.Hl.Blut	2020
ATK25-I06	Dinkelsbühl	2018
ATK25-I07	Wassertrüdingen	2021
ATK25-I08	Gunzenhausen	2018
ATK25-I09	Weißenburg i.Bay.	2019
ATK25-I10	Hilpoltstein	2019
ATK25-I11	Beilngries	2019
ATK25-I12	Hemau	2018
ATK25-I13	Regensburg-Nord	2018
ATK25-I14	Regenstauf	2018
ATK25-I15	Roding	2018
ATK25-I16	Bad Kötzting	2018
ATK25-I17	Viechtach	2019
ATK25-I18	Zwiesel	2019
ATK25-I19	Frauenau	2019
ATK25-J07	Nördlingen	2018
ATK25-J08	Treuchtlingen	2021
ATK25-J09	Pappenheim	2020
ATK25-J10	Eichstätt	2020
ATK25-J11	Denkendorf	2020
ATK25-J12	Kelheim	2020
ATK25-J13	Regensburg-Süd	2018
ATK25-J14	Neutraubling	2018
ATK25-J15	Straubing	2018
ATK25-J16	Bogen	2017
ATK25-J17	Ruhmannsfelden	2017
ATK25-J18	Regen	2017
ATK25-J19	Grafenau	2017
ATK25-J20	Mauth	2017
ATK25-K07	Bissingen	2018
ATK25-K08	Donauwörth	2016
ATK25-K09	Rain	2021
ATK25-K10	Neuburg a.d.Donau	2020
ATK25-K11	Ingolstadt	2020
ATK25-K12	Abensberg	2020
ATK25-K13	Rottenburg a.d.Laaber	2018
ATK25-K14	Mallersdorf-Pfaffenberg	2018
ATK25-K15	Geiselhöring	2018
ATK25-K16	Landau a.d.Isar	2018
ATK25-K17	Deggendorf	2017
ATK25-K18	Schöllnach	2017
ATK25-K19	Freyung	2017
ATK25-K20	Waldkirchen	2017
ATK25-L06	Lauingen (Donau)	2018
ATK25-L07	Dillingen a.d.Donau	2017
ATK25-L08	Wertingen	2016
ATK25-L09	Pöttmes	2021
ATK25-L10	Schrobenhausen	2020
ATK25-L11	Pfaffenhofen a.d.Ilm	2020
ATK25-L12	Mainburg	2020
ATK25-L13	Pfeffenhausen	2018
ATK25-L14	Landshut	2018
ATK25-L15	Dingolfing	2018
ATK25-L16	Reisbach	2018
ATK25-L17	Eichendorf	2018
ATK25-L18	Vilshofen an der Donau	2018
ATK25-L19	Passau	2018
ATK25-L20	Hauzenberg	2018
ATK25-M05	Neu-Ulm	2018
ATK25-M06	Günzburg	2018
ATK25-M07	Zusmarshausen	2017
ATK25-M08	Augsburg	2016
ATK25-M09	Aichach	2021
ATK25-M10	Markt Indersdorf	2020
ATK25-M11	Petershausen	2020
ATK25-M12	Freising	2019
ATK25-M13	Moosburg a.d.Isar	2019
ATK25-M14	Vilsbiburg	2019
ATK25-M15	Neumarkt-Sankt Veit	2019
ATK25-M16	Eggenfelden	2019
ATK25-M17	Pfarrkirchen	2019
ATK25-M18	Bad Griesbach i.Rottal	2019
ATK25-M19	Pocking	2019
ATK25-N05	Illertissen	2018
ATK25-N06	Krumbach (Schwaben)	2017
ATK25-N07	Thannhausen	2016
ATK25-N08	Königsbrunn	2016
ATK25-N09	Mering	2021
ATK25-N10	Fürstenfeldbruck	2020
ATK25-N11	München-Nord	2020
ATK25-N12	Garching b.München	2019
ATK25-N13	Erding	2019
ATK25-N14	Dorfen	2019
ATK25-N15	Mühldorf a.Inn	2019
ATK25-N16	Altötting	2019
ATK25-N17	Simbach a.Inn	2019
ATK25-N18	Bad Füssing	2019
ATK25-O05	Memmingen	2018
ATK25-O06	Erkheim	2017
ATK25-O07	Mindelheim	2016
ATK25-O08	Landsberg am Lech	2021
ATK25-O09	Ammersee	2021
ATK25-O10	Starnberg	2019
ATK25-O11	München-Süd	2018
ATK25-O12	Vaterstetten	2018
ATK25-O13	Ebersberg	2018
ATK25-O14	Wasserburg a.Inn	2018
ATK25-O15	Trostberg	2018
ATK25-O16	Tittmoning	2018
ATK25-P05	Bad Grönenbach	2018
ATK25-P06	Ottobeuren	2017
ATK25-P07	Kaufbeuren	2017
ATK25-P08	Schongau	2021
ATK25-P09	Weilheim i.OB	2021
ATK25-P10	Starnberger See	2019
ATK25-P11	Wolfratshausen	2018
ATK25-P12	Holzkirchen	2018
ATK25-P13	Rosenheim	2020
ATK25-P14	Bad Endorf	2016
ATK25-P15	Chiemsee	2020
ATK25-P16	Traunstein	2018
ATK25-P17	Freilassing	2018
ATK25-Q04	Lindenberg i.Allgäu	2018
ATK25-Q05	Weitnau	2018
ATK25-Q06	Kempten (Allgäu)	2017
ATK25-Q07	Marktoberdorf	2017
ATK25-Q08	Halblech	2017
ATK25-Q09	Peißenberg	2017
ATK25-Q10	Murnau a.Staffelsee	2017
ATK25-Q11	Bad Tölz	2017
ATK25-Q12	Tegernsee	2017
ATK25-Q13	Bayrischzell	2016
ATK25-Q14	Aschau i.Chiemgau	2016
ATK25-Q15	Reit im Winkl	2016
ATK25-Q16	Ruhpolding	2019
ATK25-Q17	Bad Reichenhall	2019
ATK25-R03	Lindau (Bodensee)	2018
ATK25-R04	Scheidegg	2018
ATK25-R05	Oberstaufen	2017
ATK25-R06	Sonthofen	2017
ATK25-R07	Pfronten	2017
ATK25-R08	Füssen	2017
ATK25-R09	Garmisch-Partenkirchen	2017
ATK25-R10	Wallgau	2017
ATK25-R11	Jachenau	2017
ATK25-R12	Kreuth	2017
ATK25-R16	Watzmann	2019
ATK25-R17	Königssee	2019
ATK25-S05	Hoher Ifen	2017
ATK25-S06	Oberstdorf	2017
ATK25-S09	Zugspitze	2017
ATK25-S10	Mittenwald	2017

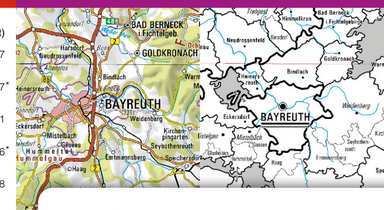
Auflistung der UK50-Kartenblätter

Blattnr.	Name	Erscheinungsjahr (*Neuauflage in Arbeit)
UK50-1	Naturpark Bayerische Rhön Bad Kissingen – Hammelburg – Bad Neustadt a.d.Saale – Bad Brückenau – Mellrichstadt – Bischofsheim a.d.Rhön	2020
UK50-2	Naturpark Haßberge Schweinfurt – Bad Neustadt a.d.Saale – Haßfurt – Münnerstadt – Ebern – Eltmann – Bad Königshofen i.Grabfeld – Zeil am.Main	2020
UK50-3	Coburger Land – Oberes Maintal – Bamberg Lichtenfels – Kronach – Neustadt b.Coburg – Hirschaid – Kloster Banz – Bad Staffelstein – Itzgrund	2021
UK50-4	Naturpark Frankenwald Kulmbach – Kronach – Helmbrechts – Neustadt b.Coburg – Naila – Münchberg – Bad Lobenstein – Schwarzenbach a.Wald – Weismain – Bad Berneck – Gefrees – Saalburg	2020
UK50-5	Hof – Selb – Aš Münchberg – Naila – Rehau – Naturpark Frankenwald, östl. Teil – Naturpark Fichtelgebirge, nördl. Teil	2017
UK50-6	Naturpark Spessart, nördlicher Teil Aschaffenburg – Hanau – Karlstadt – Sinngrund	2018
UK50-7	Fränkisches Weinland Würzburg – Schweinfurt – Kitzingen – Maindreieck	2019
UK50-8	Naturpark Steigerwald, nördlicher Teil Bamberg – Schweinfurt – Haßfurt – Volkach – Hallstadt – Gerolzhofen – Schlüsselfeld – Eltmann – Zeil a.Main	2020
UK50-9	Naturpark Steigerwald, südlicher Teil Erlangen – Herzogenaurach – Kitzingen – Fürth – Höchstadt a.d.Aisch – Bad Windsheim – Neustadt a.d.Aisch – Langenzenn – Uffenheim	2020
UK50-10	Naturpark Fränkische Schweiz-Veldensteiner Forst, nördl.Teil Bayreuth – Kulmbach	2017
UK50-11	Naturpark Fränkische Schweiz-Veldensteiner Forst, südl.Teil Erlangen – Lauf an der Pegnitz	2018
UK50-12	Naturpark Fichtelgebirge, westl.Teil Bayreuth – Bad Berneck – Kemnath – Münchberg	2017
UK50-13	Naturpark Fichtelgebirge, östl.Teil – Naturpark Steinwald Stiftland – Tirschenreuth – Cheb	2017
UK50-14	Naturpark Nördlicher Oberpfälzer Wald Auerbach i.d.OPf. – Sulzbach-Rosenberg – Weiden i.d.OPf. – Windischeschenbach	2018
UK50-16	Naturpark Spessart, südlicher Teil Unteres Taubertal – Geo-Naturpark Bergstraße-Odenwald – Naturpark Neckartal-Odenwald	2018
UK50-17	Naturpark Frankenhöhe Rothenburg o.d.T. – Ansbach	2018
UK50-18	Nürnberger Land – Frankenalb Nürnberg – Fürth – Erlangen – Schwabach – Lauf a.d.Pegnitz	2018
UK50-19	Naturpark Hirschwald Amberg – Neumarkt i.d.OPf. – Sulzbach-Rosenberg	2019
UK50-20	Naturpark Oberpfälzer Wald Schwandorf – Burglengenfeld – Neunburg vorm Wald – Oberviechtach – Oberpfälzer Seenland	2018
UK50-21	Ries – Nördlingen – Dinkelsbühl Hesselberg – Altmühlsee	2018
UK50-22	Fränkisches Seenland Brombachsee – Altmühlsee – Rothsee – Igelsbachsee – Hahnenkammsee – Weißenburg i.Bay. – Hilpoltstein	2018
UK50-23	Naturpark Altmühltal, westlicher Teil Gunzenhausen – Weißenburg i.Bay. – Solnhofen – Altmühl- u. Brombachsee	2018
UK50-24	Naturpark Altmühltal, mittlerer Teil Eichstätt – Greding – Beilngries – Kipfenberg – Neuburg a.d.Donau – Ingolstadt	2018
UK50-25	Naturpark Altmühltal, östlicher Teil Regensburg – Kelheim – Mainburg – Neustadt a.d.Donau – Riedenburg	2019
UK50-26	Naturpark Oberer Bayerischer Wald, westl. Teil Regensburg – Schwandorf – Straubing West	2017*
UK50-27	Naturpark Oberer Bayerischer Wald, östl. Teil Bad Kötzting – Cham – Furth im Wald – Waldmünchen – Lamer Winkel	2017*
UK50-28	Naturpark Bayerischer Wald, westlicher Teil Straubing – Deggendorf – Regen – Viechtach	2016*
UK50-29	Nationalpark Bayerischer Wald – Naturpark östlicher Teil – Nationalpark Šumava Regen – Zwiesel – Grafenau – Spiegelau – Bodenmais – Frauenau – Großer Rachel – Großer Arber – Lusen	2021
UK50-30	Naturpark Bayerischer Wald, südlicher Teil Passau – Deggendorf – Vilshofen – Freyung	2017*
UK50-31	Günzburg – Donauried Ulm – Neu-Ulm – Dillingen a.d.Donau – Illertissen – Krumbach – Giengen a.d.B.	2019
UK50-32	Naturpark Augsburg-Westliche Wälder Friedberg – Königsbrunn – Gersthofen – Neusäß – Dillingen a.d.D. – Bobingen – Schwabmünchen – Meitingen – Donauried	2021
UK50-34	Landkreise Pfaffenhofen a.d.Ilm – Neuburg-Schrobenhausen Ingolstadt – Eichstätt – Manching – Wolnzach – Geisenfeld – Vohburg a.d.Donau – Reichertshofen – Pöttmes – Allershausen – Wellheim – Donaumoos	2021
UK50-35	Landshut Dingolfing – Moosburg a.d.Isar – Mainburg – Vilsbiburg – Taufkirchen (Vils) – Rottenburg a.d.Laaber – Neumarkt-Sankt Veit – Au i.d.Hallertau – Burg Trausnitz	2021
UK50-36	Landkreis Dingolfing-Landau Deggendorf – Plattling – Osterhofen – Vilstal	2016*
UK50-37	Rottaler Bäderdreieck Bad Birnbach – Bad Füssing – Bad Griesbach	2018
UK50-38	Kneippland® Unterallgäu Kaufbeuren – Memmingen – Illertissen – Bad Wörishofen – Mindelheim – Krumbach – Buchloe – Ottobeuren – Bad Grönenbach	2020
UK50-39	Kaufbeuren Landsberg am Lech – Marktoberdorf – Mindelheim – Bad Wörishofen – Buchloe – Schongau – Peiting – Hohenpeißenberg – Obergünzburg – Wilpoldsried – Wessobrunn – Irsee	2021
UK50-40	München Nord und West Freising – Dachau – Germering – Erding – Fürstenfeldbruck – Unterschleißheim – Gröbenzell – Garching b.München	2021
UK50-41	Ammersee – Starnberger See – München Süd Starnberg – Weilheim i.OB – Wolfratshausen – Holzkirchen – Herrsching a.A. – Dießen a.A. – Tutzing – Schäftlarn – Weyarn – Andechs – Raisting	2021
UK50-42	München-Ost Erding – Garching – Dorfen – Grafing – Markt Schwaben – Ebersberg – Taufkirchen (Vils) – Isen – Speichersee – Ebersberger Forst – Flughafen München	2020
UK50-44	Inn-Salzach-Region – Rupertiwinkel – Östlicher Chiemgau Waldkraiburg – Traunstein – Burghausen – Mühldorf a.Inn – Altötting – Waginger See	2020
UK50-45	Lindau – Naturpark Nagelfluhkette Wangen – Immenstadt – Isny – Lindenberg – Oberstaufen – Weitnau – Scheidegg – Hoher Ifen – Fellhorn – Riedberger Horn – Großer Alpsee – Bregenz	2021
UK50-46	Kempten (Allgäu) Bad Grönenbach – Immenstadt – Nesselwang – Pfronten	2016*
UK50-47	Allgäuer Alpen Sonthofen – Immenstadt i.Allgäu – Pfronten – Oberstdorf – Oberstaufen – Blaichach – Bad Hindelang – Rettenberg – Fischen i.Allgäu – Mädelegabel – Hochvogel – Hoher Ifen – Nebelhorn	2021
UK50-48	Füssen Pfronten – Reutte – Nesselwang – Halblech – Steingaden – Forggensee – Neuschwanstein – Hohenschwangau – Ammergauer Alpen – südl.Auerbergland	2020
UK50-49	Pfaffenwinkel – Ammergauer Alpen Nord Weilheim – Peißenberg – Schongau – Murnau a.Staffelsee – Peiting – Oberammergau – Bad Kohlgrub – Ettal – Linderhof – Staffelsee	2021
UK50-50	Werdenfelser Land Naturpark Ammergauer Alpen – Garmisch-Partenkirchen – Mittenwald – Murnau a.Staffelsee – Oberammergau – Wettersteinstein – Zugspitze	2019
UK50-51	Karwendel Garmisch-Partenkirchen – Lenggries – Murnau a.Staffelsee – Mittenwald – Kochelsee und Walchensee – Sylvensteinsee – Achensee	2019
UK50-52	Tölzer Land – Starnberger See Starnberg – Wolfratshausen – Bad Tölz – Penzberg – Holzkirchen – Lenggries – Kochelsee – Walchensee	2019
UK50-53	Mangfallgebirge Rosenheim – Bad Aibling – Kolbermoor – Bayrischzell – Holzkirchen – Kiefersfelden – Inntal – Tegernsee – Schliersee	2019
UK50-54	Chiemsee – Chiemgauer Alpen Traunstein – Wasserburg a.Inn – Bad Endorf – Prien a.Chiemsee – Haag i.OB – Ruhpolding – Reit im Winkel – Simssee – Kaiserwinkel	2019
UK50-55	Berchtesgadener Alpen Bad Reichenhall – Königssee – Hallein – Saalfelden – Lofer – Inzell – Nationalpark Berchtesgaden – Golling a.d.S. – Steinernes Meer	2019

Auflistung der ATK100-Kartenblätter

Blattnr.	Name	Erscheinungsjahr (*Neuauflage in Arbeit)
ATK100-1	Spessart Würzburg – Aschaffenburg	2017
ATK100-2	Bayerische Rhön Schweinfurt – Würzburg – Lohr a.Main	2017*
ATK100-3	Bamberg – Coburg Haßberge – Kronach – Kulmbach – Kloster Banz	2021
ATK100-4	Fichtelgebirge Hof – Bayreuth	2016*
ATK100-5	Nürnberg West Steigerwald – Rothenburg ob der Tauber	2018
ATK100-6	Nürnberg Ost Fränkische Schweiz – Bayreuth – Amberg	2018
ATK100-7	Oberpfälzer Wald Weiden i.d.OPf. – Amberg – Cham	2021
ATK100-8	Fränkisches Seenland Ansbach – Nördlingen – Donauwörth	2017*
ATK100-9	Altmühltal Ingolstadt – Eichstätt – Kelheim – Neumarkt i.d.OPf.	2021
ATK100-10	Regensburg Gäuboden – Dingolfing – Furth im Wald	2020
ATK100-11	Bayerischer Wald Deggendorf – Passau – Bad Kötzting	2020
ATK100-12	Augsburg – Ulm Memmingen – Landsberg am Lech – Donauried	2020
ATK100-13	München Nord Hallertau	2018
ATK100-14	Landshut München Ost – Burghausen – Wasserburg	2019
ATK100-15	Rottal – Inn Passau – Mühldorf a.Inn	2019
ATK100-16	Allgäu Memmingen – Kaufbeuren – Oberstdorf – Lindau	2017
ATK100-17	Pfaffenwinkel – Ostallgäu Landsberg am Lech – Fünfseenland – Füssen – Werdenfelser Land	2019
ATK100-18	München Süd Mittenwald – Bad Tölz – Kufstein	2018
ATK100-19	Chiemgau Rosenheim – Rupertiwinkel – Königssee	2019

Übersichtskarte von Bayern 1 : 500 000 (ÜK500 Bayern)




Bayern im Überblick

Die ÜK500 Bayern stellt ganz Bayern im Maßstab 1 : 500 000 übersichtlich auf einem Kartenblatt dar.
Neben der Ausgabe mit physischer Darstellung Bayerns und Ortsregister auf der Rückseite ist auch eine Version mit den bayerischen Verwaltungsgrenzen erhältlich.

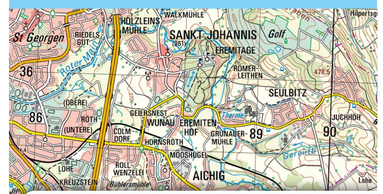
- **Kartenbildformat: ca. 72 cm x 75,4 cm**
- **ganz Bayern auf einer Karte**
- **mit Ortsregister**

Weitere Infos zu den erhältlichen Blättern finden Sie im Internet unter

https://www.ldbv.bayern.de/produkte/topo/uebersicht.html



Topographische Karte 1 : 50 000 TK-Rahmenblätter



Jedes Rahmenblatt 1 : 50 000 bildet ca. 520 km² Landschaftsfläche ab. Im Gegensatz zur Umgebungskarte 1 : 50 000 (UK50) sind keine Freizeitinformationen im Kartenblatt enthalten. Der Blattschnitt ist regelmäßig, die Blätter fügen sich ohne Überlappungsbereich nahtlos aneinander.

Der Auflagendruck der Rahmenblätter wurde eingestellt, vorhandene TK50-Blätter stehen aber noch im Buchhandel zur Verfügung. Weitere Infos zur Blatteinteilung und zu den erhältlichen Blättern finden Sie im Internet unter

http://www.ldbv.bayern.de/produkte/topo/uk.html



Bezugsquellen

Die gefalteten Karten sind über den örtlichen Buchhandel sowie über den Online-Buchhandel erhältlich. Ungefaltete Karten sind ausschließlich über die Buchhandlung Biazza OHG (Kontaktdaten siehe unten) zu beziehen.

für Wiederverkäufer:

Gefaltete Karten erhalten Sie über GeoCenter T&M,
Touristik Medienservice GmbH
Kurze Straße 40
70794 Filderstadt
Telefon: 0711 78194610
Fax: 0711 7824375
E-Mail: vertrieb@geocenter.de
Internet: www.geocenter.de

Ungefaltete Karten erhalten Sie über Buchhandlung Biazza OHG

Telefon: 089 235005-0
Fax: 089 235005-23
E-Mail: service@biazzamedien.de
Internet: www.biazzamedien.de

Hinweise zum Urheberrecht

Das Landesamt für Digitalisierung, Breitband und Vermessung besitzt alle Rechte an den von ihm hergestellten und laufend aktuell gehaltenen Produkten. Insbesondere besitzt es die Urheberrechte an den kartografischen Werken (§ 2 Abs. 1 Ziff. 7 sowie § 4 Urheberrechtsgesetz), die Rechte an den Luftbildern (§ 72 UrhG) und die Rechte als Datenbankhersteller (§§ 87 a–e UrhG).

Jede Nutzung der geschützten Produkte, die über die gesetzlichen Schranken hinausgeht, bedarf deshalb einer Erlaubnis. Dazu zählen die Vervielfältigung in jeder Form (z.B. Nachdruck, Kopie, Scannen, Entnahme von Daten durch Digitalisierung und Speicherung auf Datenträgern) sowie die Veröffentlichung und Weitergabe an Dritte, auch in umgearbeiteter Form. Unerlaubte Nutzungen sind nach dem Vermessungs- und Katastergesetz mit Geldbuße sowie nach dem Urheberrechtsgesetz mit Strafe bedroht.

Beim Erwerb digitaler Produkte ist der Abschluss einer allgemeinen Nutzungsvereinbarung für die interne Nutzung verpflichtend. Für eine darüber hinausgehende Nutzung oder eine Verwertung analoger Produkte ist eine besondere Nutzungserlaubnis erforderlich.